8

DepED
DEPARTMENT OF EDUCATION

Sagutang Papel ng Pagkatuto sa Araling Panlipunan

Kuwarter 1

Aralin

1

GOVERNMENT PROPERTY
NOT FOR SALE

Sagutang Papel ng Pagkatuto sa Araling Panlipunan
Kuwarter 1: Linggo 1
SY 2024-2025

Ang kagamitang panturong ito ay eksklusibo sa mga gurong kalahok para paunang papapatupad o implementasyon ng MATATAG K - 10 na kurikulum sa taong panuruang 2024-2025. Layunin nitong mailahad ang nilalaman ng kurikulum, pamantayan, at mga kasanayang dapat malinang sa mga aralin. Ang anomang walang pahintulot na pagpapalathala, pamamahagi, pagmomodipika, at paggamit ay mahigpit na ipinagbabawal at may karampatang legal na katumbas na aksiyon.

Ang mga nahiram na nilalaman na kasama sa materyales na ito ay pag-aari ng mga may karapatang-sipi. Ginawa ang lahat upang malaman ang pinagmulan at makahingi ng permiso na magamit ang mga ito mula sa nagmamay-ari ng karapatang-sipi. Ang mga tagapaglathala at pangkat ng tagabuo ay walang anomang karapatan sa pagmamay-ari para sa mga ito.

Mga Tagabuo

Manunulat:
- Arlene Joy T. Jacob

Tagasuri:
- Ma. Victoria Culminas - Colis, PhD.

Mga Tagapamahala

Philippine Normal University
Research Institute for Teacher Quality
SiMERR National Research Centre

Ang bawat pag-iingat ay ginawa upang masigurado ang katiyakan ng mga impormasyong nakapaloob sa materyales na ito. Para sa mga katanungan o fidbak, maaaring sumulat o tumawag sa Tanggapan ng Direktor ng *Bureau of Learning Resources* sa mga numero ng telepono (02) 8634-1072 and 8631-6922 o mag-email sa blr.od@deped.gov.ph

SAGUTANG PAPEL NG PAGKATUTO

Asignatura	Araling Panlipunan 8	**Kwarter**	1
Bilang ng Aralin	Aralin 1 (Unang Linggo)	**Petsa**	
Pamagat ng Aralin / Paksa	Heograpiya ng Asya at Daigdig		
Pangalan:		**Baitang at Pangkat:**	

I. Gawain: AROUND THE WORLD

II. Mga Layunin:

1. Natutukoy ang mga kinaroroonan ng mga kilalang *landmarks sa* buong daigdig*;*
2. Nakagagawa ng isang pananaliksik sa mga bansa na nais puntahan ng mag-aaral; at
3. Nakasusulat ng journal tungkol sa kahalagahan at implikasyon ng pag-aaral ng heograpiya sa pamumuhay ng mga tao.

III. Mga Kailangang Materyales: Sagutang papel, mapa ng daigdig

IV. Panuto: AROUND THE WORLD: Tukuyin ang mga kontinente sa Daigdig kung saan makikita ang mga kilalang *landmark* na ipinapakita sa bawat larawan.

https://commons.wik

_____

https://commons.wi

_____

https://www.worldhi

_____

https://www.pexels.c

_____

https://commons.wi

_____

https://commons.wik

https://commons

SAGUTANG PAPEL NG PAGKATUTO

Asignatura	Araling Panlipunan 8	**Kwarter**	1
Bilang ng Aralin	Aralin 1 (Unang Linggo)	**Petsa**	
Pamagat ng Aralin / Paksa	Heograpiya ng Asya at Daigdig		
Pangalan:		**Baitang at Pangkat:**	

I. Gawain: SALIKSIK-SURI

II. Mga Layunin:

1. Natutukoy ang mga kinaroroonan ng mga kilalang *landmarks sa* buong daigdig*;*
2. Nakagagawa ng isang pananaliksik sa mga bansa na nais puntahan ng mag-aaral; at
3. Nakasusulat ng journal tungkol sa kahalagahan at implikasyon ng pag-aaral ng heograpiya sa pamumuhay ng mga tao.

III. Mga Kailangang Materyales: Sagutang papel, mapa ng daigdig

IV. Panuto: Buuin ang dayagram, lagyan ng tamang impormasyon na hinihingi sa *call out*. Gamitin ang takda na ibinigay ng guro upang masagot ang gawain.

Ako si_____
Ang Bansang aking nasaliksik ay _____
Ang Klima dito ay _____

Ang mga pangunahing likas na yaman dito ay _____
Ang pangunahing hanapbuhay sa bansang ito ay

Ako si_____
Ang Bansang aking nasaliksik ay _____
Ang Klima dito ay _____

Ang mga pangunahing likas na yaman dito ay _____
Ang pangunahing hanap buhay sa bansang ito ay _____



SAGUTANG PAPEL NG PAGKATUTO

Asignatura	Araling Panlipunan 8	**Kwarter**	1
Bilang ng Aralin	Aralin 1 (Unang Linggo)	**Petsa**	
Pamagat ng Aralin / Paksa	Heograpiya ng Asya at Daigdig		
Pangalan:		**Baitang at Pangkat:**	

I. Gawain A: LIMANG TEMA NG HEOGRAPIYA

II. Mga Layunin:

1. Natutukoy ang mga kinaroroonan ng mga kilalang *landmarks sa* buong daigdig*;*
2. Nakagagawa ng isang pananaliksik sa mga bansa na nais puntahan ng mag-aaral; at
3. Nakasusulat ng journal tungkol sa kahalagahan at implikasyon ng pag-aaral ng heograpiya sa pamumuhay ng mga tao.

III. Mga Kailangang Materyales: Sagutang papel, mapa ng daigdig

IV. Panuto: Pumili ng isang bansa na bibigyang pansin ng inyong pangkat. Suriin ang kalagayang Heograpiko ng napiling bansa gaya ng mga konkretong halimbawa na naaayon sa limang tema ng Heograpiya. Maaaring gumamit ng iba't ibang klase ng *chart / graphic organizer* upang ipakita ito.

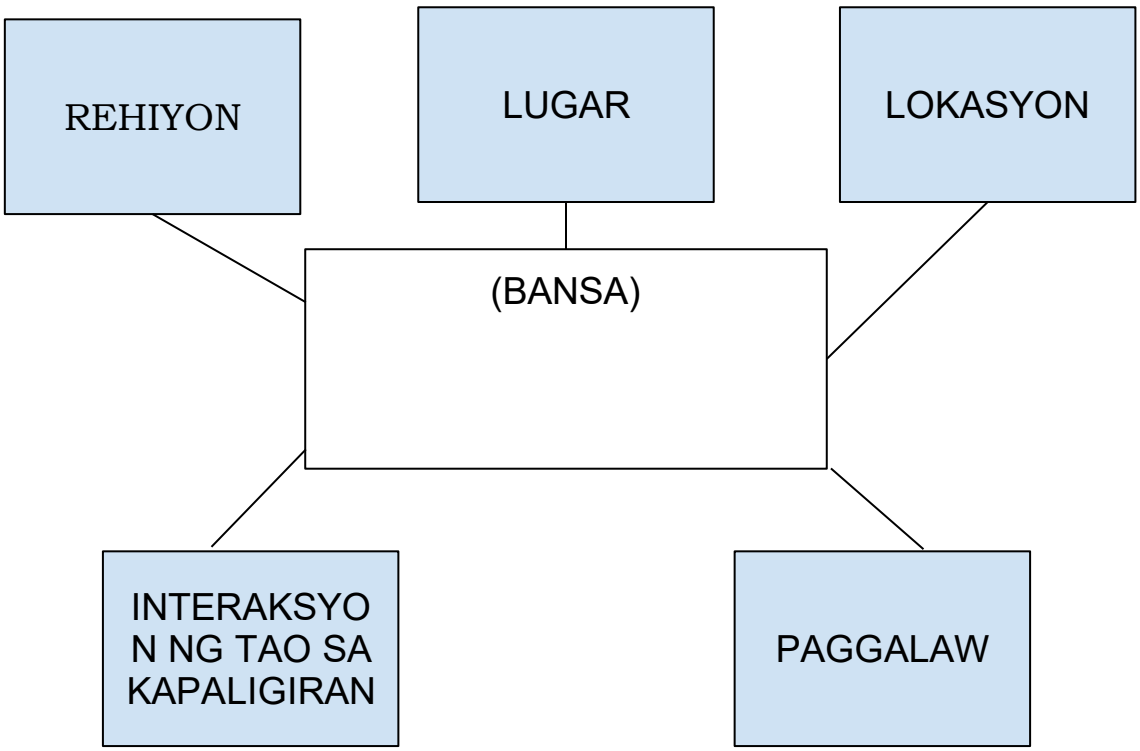

Gawain B:

Panuto: Gamit ang mapa na nasa ibaba. Isulat sa loob ng kahon ang mga kontinente na itinuturo.

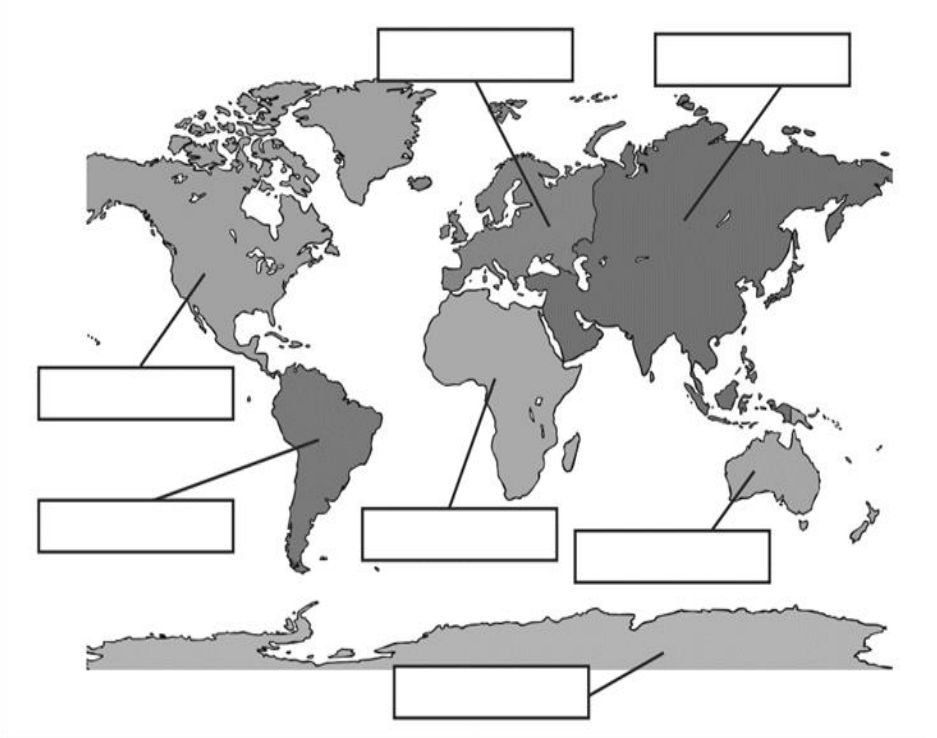

SAGUTANG PAPEL NG PAGKATUTO

Asignatura	Araling Panlipunan 8	**Kwarter**	1
Bilang ng Aralin	Aralin 1 (Unang Linggo)	**Petsa**	
Pamagat ng Aralin / Paksa	Heograpiya ng Asya at Daigdig		
Pangalan:		**Baitang at Pangkat:**	

I. Gawain A

II. Mga Layunin:

4. Natutukoy ang mga kinaroroonan ng mga kilalang *landmarks sa* buong daigdig*;*
5. Nakagagawa ng isang pananaliksik sa mga bansa na nais puntahan ng mag-aaral; at
6. Nakasusulat ng journal tungkol sa kahalagahan at implikasyon ng pag-aaral ng heograpiya sa pamumuhay ng mga tao.

III. Mga Kailangang Materyales: Sagutang papel, mapa ng daigdig

IV. **Panuto:** Gumawa ng *Journal Entry* para sa kahalagahan at implikasyon ng pag-aaral ng Heograpiya sa pamumuhay ng tao. Magbigay ng mga halimbawa. Ang *Journal entry* ay dapat na hindi bababa sa limang pangungusap.

Pangalan: _____

Baitang at Seksyon: _____ Petsa: _____

Guro: _____

Journal

_____

_____
_____
_____
_____
_____
_____
_____
_____
_____
_____
_____
_____
_____
_____
_____
_____

Gawain B:

Panuto: A. Hanapin sa Hanay B ang mga sagot sa mga tanong na nasa Hanay A.

HANAY A	HANAY B
1.Ito ang pinakamalaking kontinente	A.Asya
2.Dito sa bansang ito makikita ang *Great Wall.*	B.bulubundukin
3.Dito sa bansang ito makikita ang *Christ the Redeemer.*	C. Brazil
4. Ang teoryang ito ay pinanukala ni Alfred Wegener noong 1912 .	D.China
5.Ito ang pinakamataas na bundok sa buong mundo.	E.Continental Drift Theory
6.Ito ay hanay ng magkakarugtong na bundok.	F.lokasyong absolute
7.Ito ay paraan ng pagtukoy ng mga lugar na gumagamit ng mga imahinaryong guhit.	G.lokasyong relatibo
8.Ito ay bahagi ng daigdig na pagbubuklod buklod ng magkakatulad na katangiang pisikal at kultura.	H.lugar
9.Ito ay paraan ng pagtukoy sa isang lugar na nakabase sa mga nakapaligid dito.	I.klima
10. Ito ay tumutukoy sa katangiang natatangi sa isang pook.	J.Mt. Everest
	K. rehiyon

Gawain C:
Panuto: Ipaliwanag ang kahalagahan ng pagtukoy ng lokasyon ng isang lugar at epekto ng heograpiya sa pamumuhay ng tao. Maaaring magbigay ng mga karanasan na maaring gamitin upang ipaliwanag ito. (10 puntos)